2008年11月

保存版

八潮市
洪水ハザードマップ

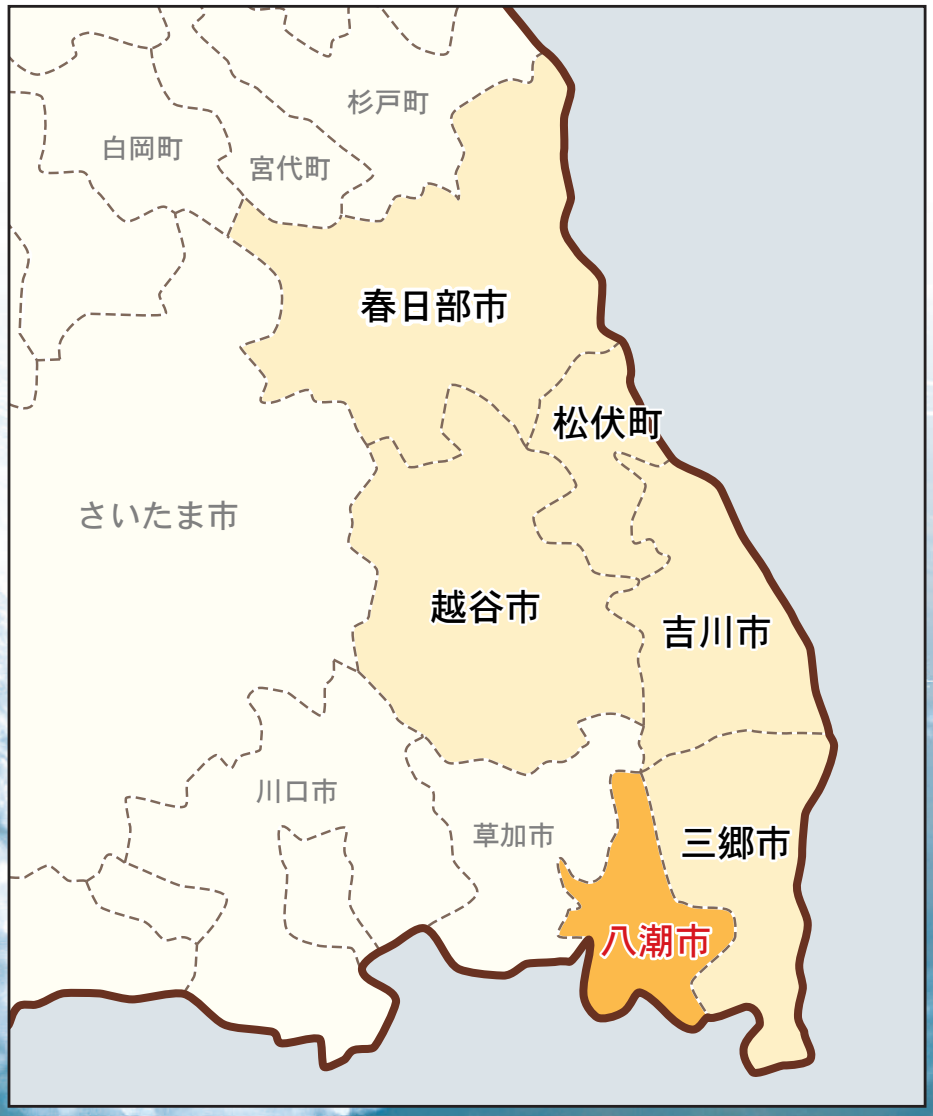

埼玉県南東部広域洪水ハザードマップ作成協議会
（構成：春日部市、越谷市、八潮市、三郷市、吉川市、松伏町 及び江戸川水防事務組合）

はじめに

このたび、八潮市では利根川、江戸川、荒川、中川・綾瀬川・元荒川の6河川で洪水が発生した際に予想される浸水や避難に関する情報を地図上に分かりやすくまとめた「八潮市洪水ハザードマップ」を、国土交通省、埼玉県のご協力を頂き作成しました。

この地図は、八潮市に隣接する河川が大雨（200年に1回程度又は100年に1回程度）により堤防が決壊したと仮定しておこなった浸水予想結果をもとに浸水する範囲、避難場所を示しておりますので、万が一の場合に備えて、日頃から様々な事態を想定して、避難場所や避難経路を確かめておくことが必要です。

この洪水ハザードマップを常に身近な場所に置き、洪水が発生するおそれのある時や洪水が発生した時に、あわてず落ち着いて安全に避難できるよう、家庭や地域、職場などでご活用ください。

平成5年8月　台風11号被害状況

目　次

- 洪水ハザードマップとは・・・

～もし、利根川がはん濫したら～

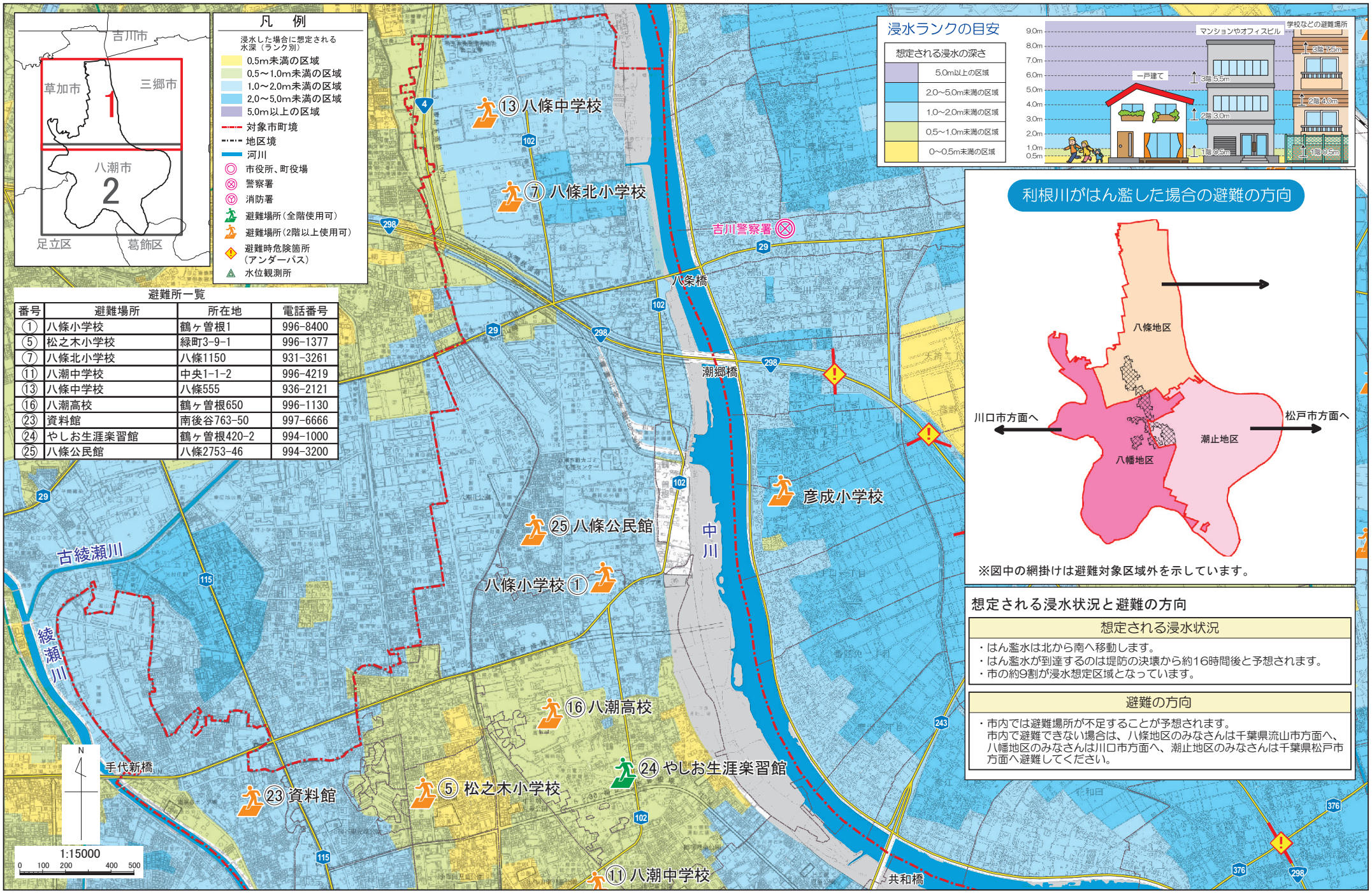

避難所一覧

番号	避難場所	所在地	電話番号
①	八條小学校	鶴ヶ曽根1	996-8400
⑤	松之木小学校	緑町3-9-1	996-1377
⑦	八條北小学校	八條1150	931-3261
⑪	八潮中学校	中央1-1-2	996-4219
⑬	八條中学校	八條555	936-2121
⑯	八潮高校	鶴ヶ曽根650	996-1130
㉓	資料館	南後谷763-50	997-6666
㉔	やしお生涯楽習館	鶴ヶ曽根420-2	994-1000
㉕	八條公民館	八條2753-46	994-3200

想定される浸水状況と避難の方向

想定される浸水状況

- はん濫水は北から南へ移動します。
- はん濫水が到達するのは堤防の決壊から約16時間後と予想されます。
- 市の約9割が浸水想定区域となっています。

避難の方向

- 市内では避難場所が不足することが予想されます。
  市内で避難できない場合は、八條地区のみなさんは千葉県流山市方面へ、八幡地区のみなさんは川口市方面へ、潮止地区のみなさんは千葉県松戸市方面へ避難してください。

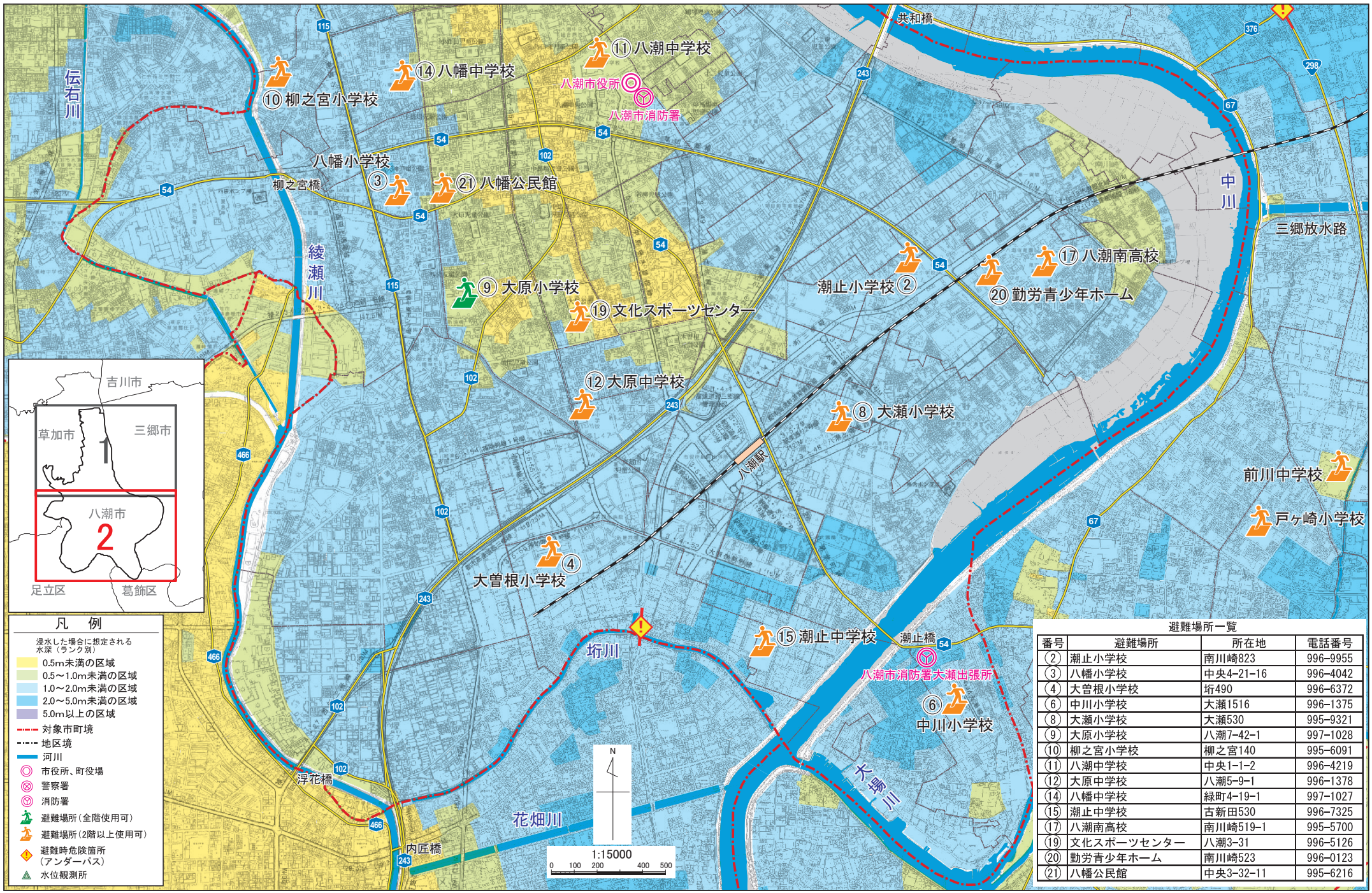

避難場所一覧

番号	避難場所	所在地	電話番号
②	潮止小学校	南川崎823	996-9955
③	八幡小学校	中央4-21-16	996-4042
④	大曽根小学校	坼490	996-6372
⑥	中川小学校	大瀬1516	996-1375
⑧	大瀬小学校	大瀬530	995-9321
⑨	大原小学校	八潮7-42-1	997-1028
⑩	柳之宮小学校	柳之宮140	995-6091
⑪	八潮中学校	中央1-1-2	996-4219
⑫	大原中学校	八潮5-9-1	996-1378
⑭	八幡中学校	緑町4-19-1	997-1027
⑮	潮止中学校	古新田530	996-7325
⑰	八潮南高校	南川崎519-1	995-5700
⑲	文化スポーツセンター	八潮3-31	996-5126
⑳	勤労青少年ホーム	南川崎523	996-0123
㉑	八幡公民館	中央3-32-11	995-6216

～もし、江戸川がはん濫したら～

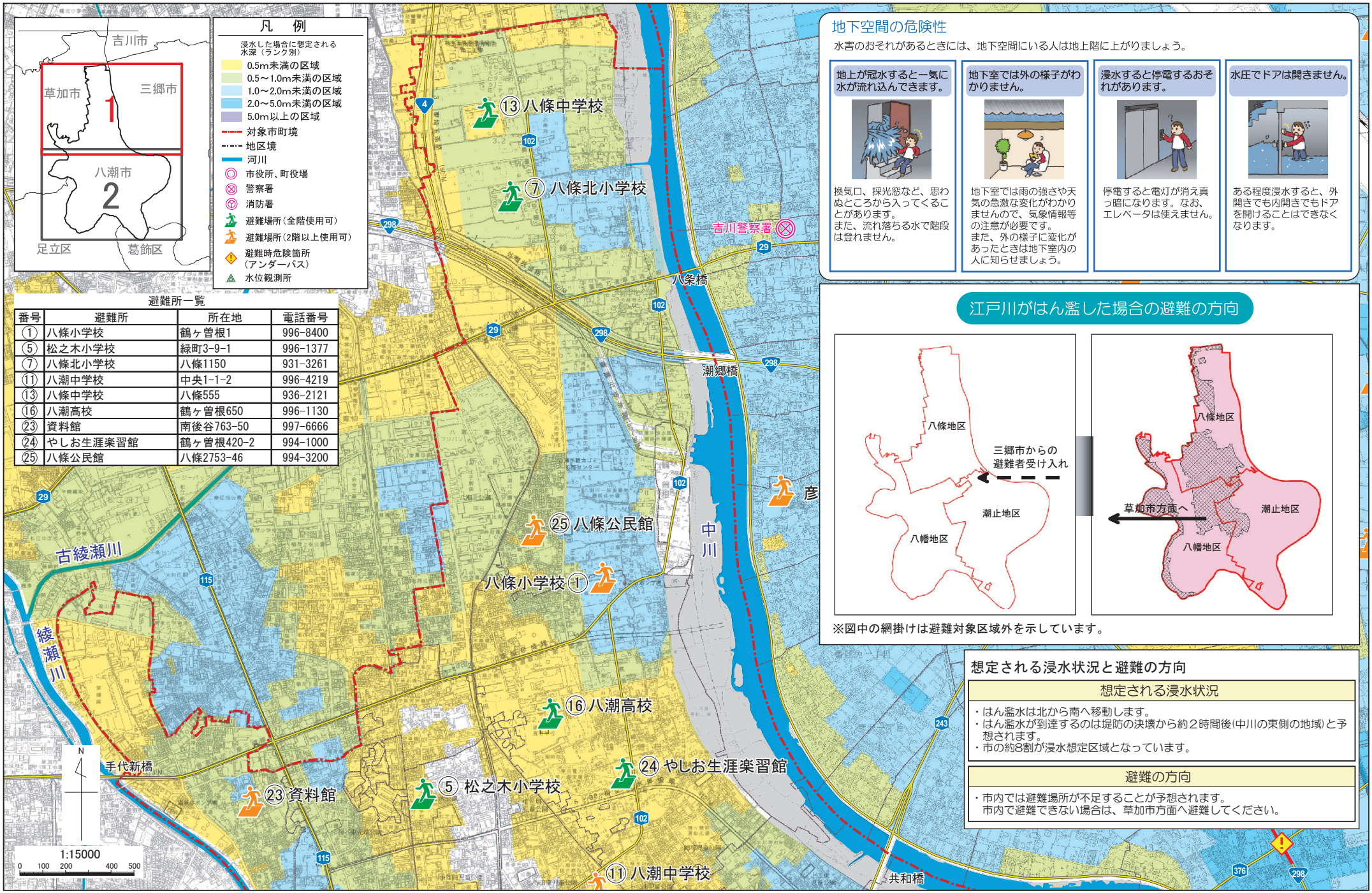

避難所一覧

番号	避難所	所在地	電話番号
①	八條小学校	鶴ヶ曽根1	996-8400
⑤	松之木小学校	緑町3-9-1	996-1377
⑦	八條北小学校	八條1150	931-3261
⑪	八潮中学校	中央1-1-2	996-4219
⑬	八條中学校	八條555	936-2121
⑯	八潮高校	鶴ヶ曽根650	996-1130
㉓	資料館	南後谷763-50	997-6666
㉔	やしお生涯楽習館	鶴ヶ曽根420-2	994-1000
㉕	八條公民館	八條2753-46	994-3200

地下空間の危険性

水害のおそれがあるときには、地下空間にいる人は地上階に上がりましょう。

地上が冠水すると一気に水が流れ込んできます。

換気口、採光窓など、思わぬところから入ってくることがあります。
また、流れ落ちる水で階段は登れません。

地下室では外の様子がわかりません。

地下室では雨の強さや天気の急激な変化がわかりませんので、気象情報等の注意が必要です。
また、外の様子に変化があったときは地下室内の人に知らせましょう。

浸水すると停電するおそれがあります。

停電すると電灯が消え真っ暗になります。なお、エレベータは使えません。

水圧でドアは開きません。

ある程度浸水すると、外開きでも内開きでもドアを開けることはできなくなります。

江戸川がはん濫した場合の避難の方向

※図中の網掛けは避難対象区域外を示しています。

想定される浸水状況と避難の方向

想定される浸水状況

- はん濫水は北から南へ移動します。
- はん濫水が到達するのは堤防の決壊から約２時間後(中川の東側の地域)と予想されます。
- 市の約8割が浸水想定区域となっています。

避難の方向

- 市内では避難場所が不足することが予想されます。
市内で避難できない場合は、草加市方面へ避難してください。

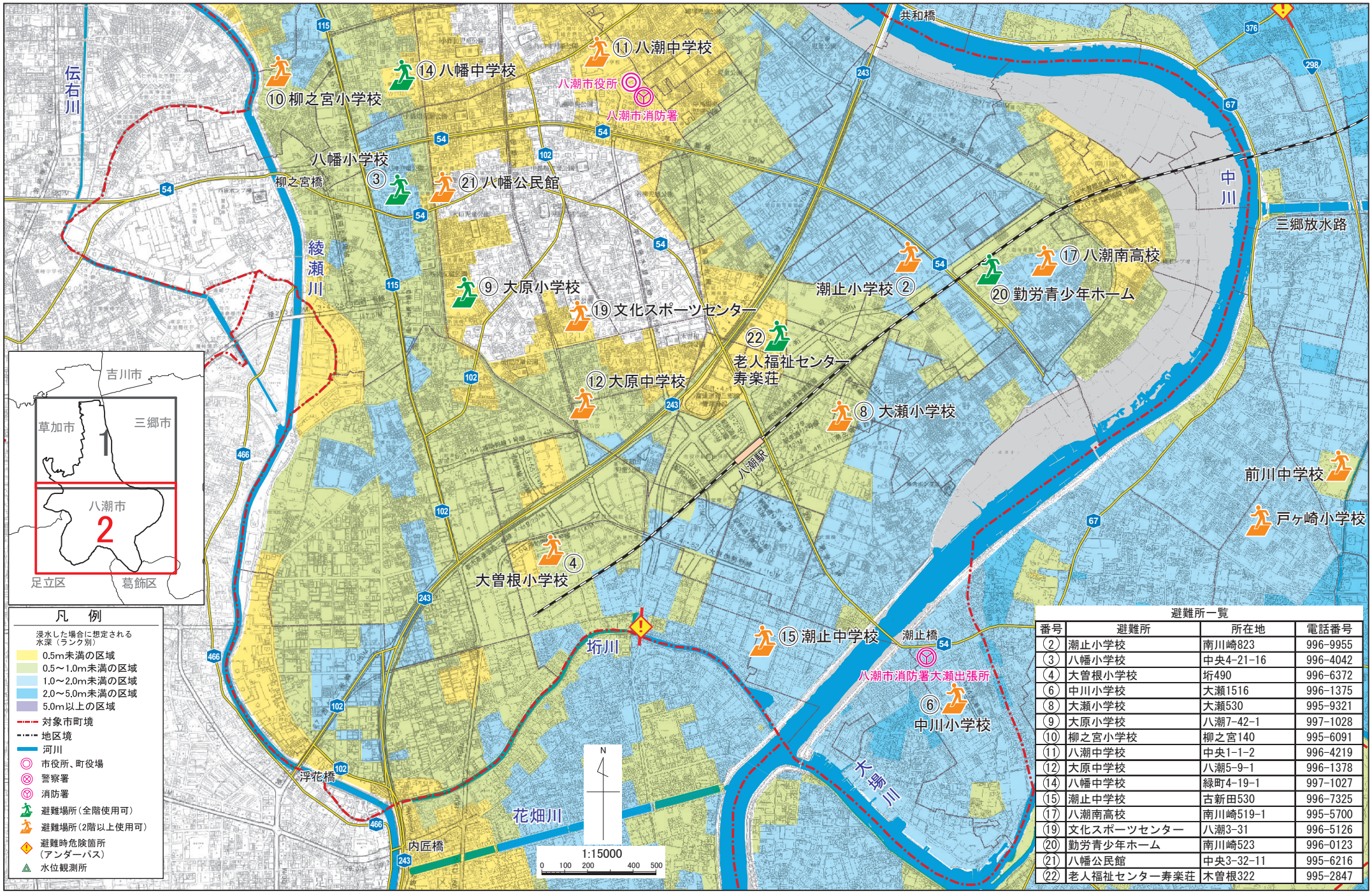

避難所一覧

番号	避難所	所在地	電話番号
②	潮止小学校	南川崎823	996-9955
③	八幡小学校	中央4-21-16	996-4042
④	大曽根小学校	坼490	996-6372
⑥	中川小学校	大瀬1516	996-1375
⑧	大瀬小学校	大瀬530	995-9321
⑨	大原小学校	八潮7-42-1	997-1028
⑩	柳之宮小学校	柳之宮140	995-6091
⑪	八潮中学校	中央1-1-2	996-4219
⑫	大原中学校	八潮5-9-1	996-1378
⑭	八幡中学校	緑町4-19-1	997-1027
⑮	潮止中学校	古新田530	996-7325
⑰	八潮南高校	南川崎519-1	995-5700
⑲	文化スポーツセンター	八潮3-31	996-5126
⑳	勤労青少年ホーム	南川崎523	996-0123
㉑	八幡公民館	中央3-32-11	995-6216
㉒	老人福祉センター寿楽荘	木曽根322	995-2847

～もし、荒川がはん濫したら～

凡　例

浸水した場合に想定される水深（ランク別）

- 0.5m未満の区域
- 0.5～1.0m未満の区域
- 1.0～2.0m未満の区域
- 2.0～5.0m未満の区域
- 5.0m以上の区域
- 対象市町境
- 地区境
- 河川
- 市役所、町役場
- 警察署
- 消防署
- 避難場所（全階使用可）
- 避難場所（2階以上使用可）
- 避難時危険箇所（アンダーパス）
- 水位観測所

※図中の網掛けは避難区域対象外を示しています。

想定される浸水状況と避難方向

想定される浸水状況

- 荒川の上流部のはん濫水は北から南へ移動します。
- 荒川の下流部のはん濫水は西から東へ移動します。
- はん濫水が到達するのは堤防の決壊から約６時間後と予想されます。
- 市の約7割が浸水想定区域となっています。

避難の方向

- 市内では避難場所が不足することが予想されます。
- 市内で避難できない場合は、八條、八幡地区のみなさんは越谷市方面へ、潮止地区のみなさんは千葉県松戸市方面へ避難してください。

～もし、中川・綾瀬川・元荒川・大落古利根川・新方川がはん濫したら～

想定される浸水状況と避難方向

想定される浸水状況

- 内水（河川に排水できずにはん濫した水）によるはん濫が想定されます。
- 市の中央は浸水しないことが想定されます。

避難の方向

- 市の北部、西部、南部の浸水深が2m以上と想定される地域、及び対象河川沿いの地域のみなさんは、市内の浸水しない区域の避難場所へ避難してください。

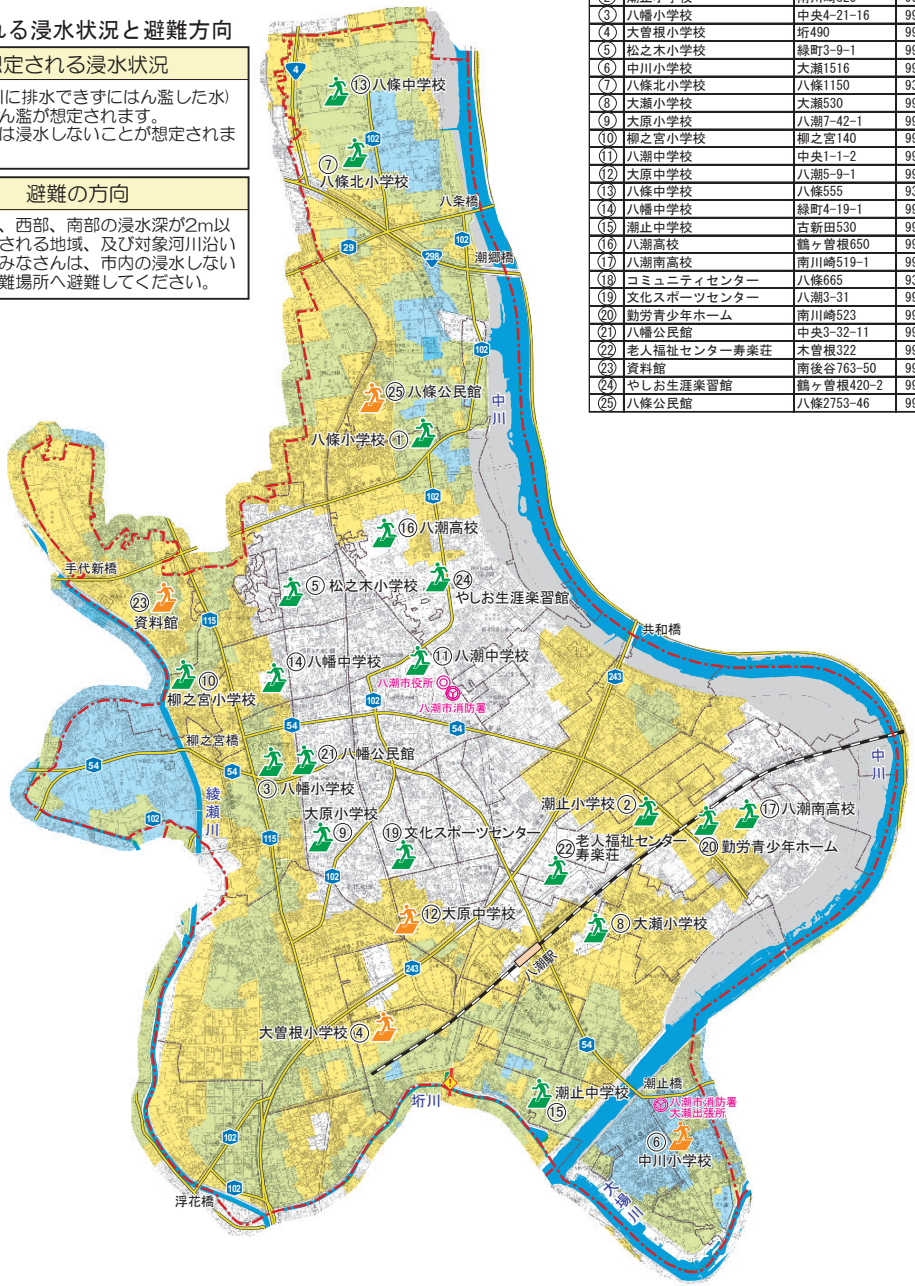

避難場所一覧

番号	避難場所	所在地	電話番号
①	八條小学校	鶴ヶ曽根1	996-8400
②	潮止小学校	南川崎823	996-9955
③	八幡小学校	中央4-21-16	996-4042
④	大曽根小学校	垳490	996-6372
⑤	松之木小学校	緑町3-9-1	996-1377
⑥	中川小学校	大瀬1516	996-1375
⑦	八條北小学校	八條1150	931-3261
⑧	大瀬小学校	大瀬530	995-9321
⑨	大原小学校	八潮7-42-1	997-1028
⑩	柳之宮小学校	柳之宮140	995-6091
⑪	八潮中学校	中央1-1-2	996-4219
⑫	大原中学校	八潮5-9-1	996-1378
⑬	八條中学校	八條555	936-2121
⑭	八幡中学校	緑町4-19-1	997-1027
⑮	潮止中学校	古新田530	996-7325
⑯	八潮高校	鶴ヶ曽根650	996-1130
⑰	八潮南高校	南川崎519-1	995-5700
⑱	コミュニティセンター	八條665	936-0507
⑲	文化スポーツセンター	八潮3-31	996-5126
⑳	勤労青少年ホーム	南川崎523	996-0123
㉑	八幡公民館	中央3-32-11	995-6216
㉒	老人福祉センター寿楽荘	木曽根322	995-2847
㉓	資料館	南後谷763-50	997-6666
㉔	やしお生涯楽習館	鶴ヶ曽根420-2	994-1000
㉕	八條公民館	八條2753-46	994-3200

わが家の避難地図をつくりましょう

▶ 浸水状況や避難場所までの経路はお住まいの地域によって異なります

洪水ハザードマップを使って、自宅から避難場所までの避難経路を記入して避難地図を作ってみましょう。

①自宅の位置を確認しましょう。

②自宅付近の浸水の深さを確認しましょう。

(　　)m～(　　)mの浸水区域　　例：(0.5)m～(1.0)mの浸水区域

③避難場所を確認して、自宅との位置関係を調べましょう。

避難経路を考える上での注意事項

○地盤が低く水が集まりやすい場所や、がけ崩れなどの土砂災害が発生する可能性のある区域は、できる限り通らないようにしましょう。

○避難時危険箇所も避けるようにしましょう。

④実際に避難することを考えて、「わが家の避難地図」欄に自宅から避難場所までの経路を書き込んでみましょう。

わが家の避難地図

記入例

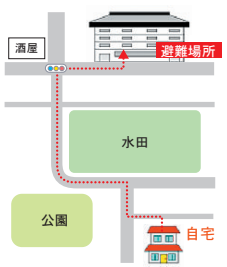

⑤家族全員で確認しましょう。

○避難地図に記入した経路を実際に歩いて、周辺の状況や所要時間を確認しましょう。

○実際の災害時は、普段と状況も異なり、避難に時間がかかることを前提に行動しましょう。

情報の伝達経路

河川のはん濫の危険性が高まった場合は、市や気象庁などから発表される情報に注意し、早めの避難を心がけましょう。

気象情報・洪水予報(注意報・警報)は次のような経路で市民のみなさんに伝達されます。

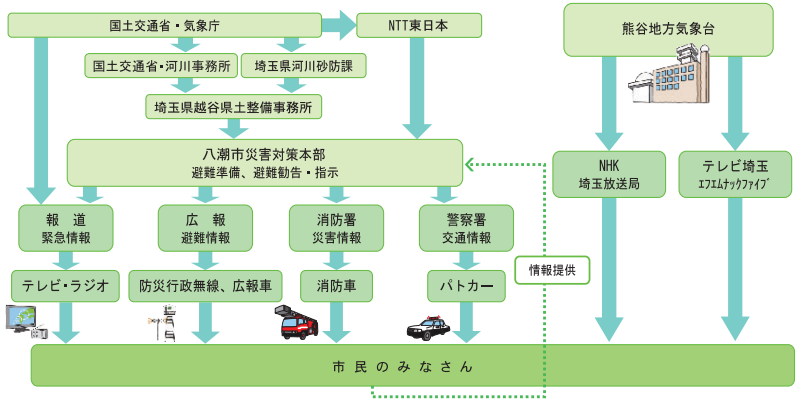

避難行動の種類

河川の水位が上昇し、はん濫の危険性が高まった場合は、河川を管理する国や県から水位や防災に関する情報が発表されます。市は、この情報を目安にして、雨の降り方などを総合的に判断した上で避難に関する情報を発表しますので、市民のみなさんは、ご家族やご近所で協力して安全に避難してください。

	利根川水位 栗橋 基準地点	江戸川水位 野田 基準地点	荒川水位 熊谷 基準地点	綾瀬川水位 谷古宇 基準地点
はん濫危険水位（危険水位）	8.50m (19.57m)	9.20m (12.61m)	5.60m (32.26m)	4.00m (4.00m)
避難判断水位（特別警戒水位）	8.00m (19.07m)	8.90m (12.31m)	4.80m (31.26m)	3.70m (3.70m)
はん濫注意水位（警戒水位）	5.00m (16.07m)	6.30m (9.71m)	3.50m (29.96m)	3.00m (3.00m)
水防団待機水位（通報水位）	2.70m (13.77m)	4.60m (8.01m)	3.00m (29.46m)	2.70m (2.70m)

※(　)書きは標高値

雨の降り方の程度

降っている雨を観察することで、だいたいの雨量を知ることができます。危険な状態になる前に自分で判断して避難ができるよう、雨の降り方と雨量の関係を知っておきましょう。雨が降り出したら、どの程度の雨なのかを観察してみるのもよいでしょう。

やや強い雨

1時間に10～20mm

地面一面に水たまりができ、話し声が聞き取りにくくなります。長雨になりそうなら警戒が必要です。

強い雨

1時間に20～30mm

傘をさしていても濡れてしまうほどの土砂降りの雨。側溝などから水があふれる心配があります。

激しい雨

1時間に30～50mm

バケツをひっくり返したような激しい雨。道路規制も行われ、避難の準備が必要です。

非常に激しい雨

1時間に50～80mm

滝のように降り、あたりが水しぶきで白っぽくなります。河川があふれる可能性がある激しい雨です。

猛烈な雨

1時間に80mm以上

滝のように降り、あたりが水しぶきで白っぽくなります。車や家屋等が水に浸かる可能性が十分強く、厳重な警戒が必要です。

▶ 注意報・警報などについて

気象台より発表される様々な情報に注意しましょう。

種類		発表の時期	警報・注意報基準
大雨	注意報	大雨によって、災害がおこる恐れがある場合	1時間雨量30mm以上または、3時間雨量50mm以上
	警報	大雨によって、重大な災害がおこる恐れがある場合	1時間雨量70mm以上
洪水	注意報	洪水によって、災害がおこる恐れがある場合	1時間雨量30mm以上かつ総雨量60mm以上 または、3時間雨量50mm以上かつ総雨量60mm以上 または、伝右川流域の流域雨量指数が5以上
	警報	洪水によって、災害がおこる恐れがある場合	1時間雨量70mm以上または、伝右川流域の流域雨量指数が9以上

※ 流域雨量指数：降雨による洪水災害発生の危険性を示す指標で、対象となる地域・時刻に存在する流域の雨量を示す指標。解析雨量、降水短時間予報をもとに、5km四方の流域ごとに算出する。

避難時の心得

万一、洪水の危険が迫ってきたら、冷静に状況判断しながら、安全な避難を心がけてください。

避難の呼びかけに注意を

危険が迫ったときには、市役所や消防署から避難の呼びかけをすることがあります。呼びかけがあった場合には、速やかに避難してください。

動きやすい服装、2人以上での避難

避難するときは、動きやすい服装で、2人以上での行動を心がけましょう。
はだし、長靴は禁物です。
動きやすい運動靴をはきましょう。

歩ける深さ男性70cm、女性50cm

歩ける深さは、男性で70cm・女性で50cmまでです。水深が腰まであるようなら高いところで救助を待ちましょう。

水面下は危険です

水面下にはどんな危険が潜んでいるかわかりません。
長い棒を杖代わりにして安全を確認しながら歩きましょう。

車での避難は控えて

自動車での避難は緊急車両の通行の妨げになりますので、特別の場合を除き、やめましょう。

▶ 災害時要援護者への協力

高齢者・病気の人には

複数の人で対応しましょう。
急を要するときはひも等を使って背負い、安全な場所へ避難しましょう。

からだの不自由な人には

それぞれの人に適した誘導方法を確認しましょう。車椅子の場合は、必ず3人で協力し、階段を上がるときは前向きに、下がるときは後ろ向きにして、恐怖感を与えないように配慮しましょう。

目の不自由な人には

「お手伝いしましょうか」などと、まず声をかけましょう。話しかける相手の声が頼りなので、話すときは、はっきりゆっくり、大きな声で、誘導するときは、杖をもっていないほうのひじのあたりを軽く触れるか、腕をかして、半歩前くらいをゆっくり歩きましょう。

耳の不自由な人には

話すときは、近くまで寄って相手にまっすぐ顔を向け、口を大きくはっきり動かしましょう。口頭でわからないようであれば、紙とペンで筆談しましょう。
紙やペンがなければ、相手の手のひらに字を書いて筆談しましょう。

普段からの備え

いざという時に備え、日頃から非常持ち出し品の準備や避難場所の確認をしておきましょう。
また、家族で避難する経路や方法など前もって避難について話し合いましょう。

避難場所や避難経路を確認しておく



この地図には、洪水時に避難する場所が示されています。自分の地区の避難場所はどこなのか、そこへ安全に行くためにはどのように避難すればいいのかを確認しておきましょう。

大雨や台風に備えて家のまわりを点検・整備

家のまわりに吹き飛ばされそうなものはないか、雨戸や雨どいなどはいたんでいないか確認しておきましょう。
また、家の前の排水溝がつまっていないかなどの確認も必要です。

非常食や持ち出す物などを準備しておく

非常食には、調理の手間がかからず、水もあまり使用しないもの(レトルト食品や缶詰等)を選びます。
また、懐中電灯やラジオ、乾電池も忘れずに用意しておきましょう。

一人暮らしの高齢者には気配りを

自分の家族や住まいだけでなく、地域全体にも目をむけましょう。
特に、一人暮らしの高齢者や病気の人たちには、日常からの気配りが必要です。

▶ 持ち出し品チェックリスト

万一の際に備えて、家庭では次のようなものを揃え、定期的にチェックしておきましょう。

■必需品

- □ 懐中電灯
- □ 携帯ラジオ・予備電池
- □ 飲料水(ミネラルウォーター)
- □ 非常食
  - □ 乾パン・缶詰
  - □ 携帯用の缶切りやナイフ
  - □ 紙コップ・紙食器 など
- □ 貴重品
  - □ 現金
  - □ 預金通帳
  - □ 印鑑
  - □ 健康保険証
  - □ 免許証(身分を証明するもの)
- □ 救急セット
  - □ ガーゼ
  - □ 脱脂綿
  - □ ばんそうこう
  - □ 目薬
  - □ きず薬
  - □ 胃腸薬
  - □ 包帯
  - □ かぜ薬 など
  - □ 消毒液
- □ タオル
- □ 衣類・下着類
- □ ロープ

■その他 必要に応じて準備しましょう

- □ 携帯電話
- □ ティッシュ
- □ 軍手
- □ ろうそく
- □ マッチ・ライター
- □ 紙おむつ
- □ ほ乳瓶・粉ミルク
- □ 介護用品
- □ 雨具
- □ ヘルメット(ずきん)
- □ レジャーシート
- □ ラップ
- □ 洗面用具
- □ 石けん
- □ ドライシャンプー など

▶ 情報の収集先

八潮市ホームページ・	http://www.city.yashio.lg.jp/
埼玉県防災情報・	http://saigaidate.pref.saitama.jp/bosai/
国土交通省 川の防災情報・	http://www.river.go.jp/
気象庁ホームページ・	http://www.jma.go.jp/
国土交通省 利根川上流河川事務所・	http://www.ktr.mlit.go.jp/tonejo/
国土交通省 江戸川河川事務所・	http://www.ktr.mlit.go.jp/edogawa/
国土交通省 荒川上流河川事務所・	http://www.ktr.mlit.go.jp/arajo/

▶ 緊急時のテレホンガイド

災害用伝言サービスを活用しよう！

●NTT災害用伝言ダイヤル「171」

局番なしの「171」にダイヤルすると、簡単な方法で伝言の録音と再生ができます。

伝言の録音　1 7 1 → 1 → ○○○(○○○)○○○○
ガイダンスが流れます　自宅の電話番号、連絡を取りたい方の電話番号

伝言の再生　1 7 1 → 2 → ○○○(○○○)○○○○

●災害用伝言板

携帯電話各社が開設する「災害用伝言板」で、安否情報の登録と確認ができます。
また、事前に設定した相手に情報を登録したことをメールで通知することもできます。
※詳しい操作方法は、携帯電話各社のホームページなどでご確認ください。

▶ 水害後、注意すること

安全の確認

LPガスボンベに異状はないか?
安全確認をする。
たばこやその他の火気厳禁。

危険物の漏れ出しはないか?
発見したら周りに注意を呼びかけ、必要に応じて消防署へも通報して適切に処理する。

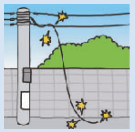

断線がないか確認。
子供たちの接近禁止。
電力会社への通報。

屋根瓦やアンテナなど、頭上の危険物を除去する。

衛生対策の徹底

浸水の後は、床下、庭、家の周りに、石灰をまいて消毒。

床上浸水があった場合は、畳や食器戸棚、食器類その他家具調度品をクレゾール石けん液で十分に拭き、日光消毒も十分する。

わが家の防災メモ

わが家の避難場所	
家族の集合場所	
災害時の連絡先	
その他の連絡先	

●家族・親戚の連絡先

家族の名前	血液型	電話番号	会社・学校名	会社・学校の連絡先
	型			
	型			
	型			
	型			
	型			
	型			
	型			

防災関係機関

機　関　名	住　所	電話番号
市役所・支所・出張所		
八潮市役所（災害対策本部）	中央1-2-1	996-2111
八潮市水道部	中央1-3-1	996-1486
医療・保健施設		
保健センター（休日診療所）	八潮8-10-1	995-3383
消防署・警察署		
八潮市消防本部・八潮市消防署	中央1-2-4	998-0119
消防署大瀬出張所	大瀬1422	997-0119
草加警察署	草加市花栗3-2-23	943-0110
八潮中央交番	中央2-12-19	996-3349
八潮北交番	鶴ヶ曽根63-5	996-3110
八潮駅前交番	大瀬757-1	997-0751
大曽根交番	大曽根270	995-6997
国・県の関係機関		
利根川上流河川事務所	栗橋町北2-19-1	0480-52-3952
江戸川河川事務所	千葉県野田市宮崎134	04-7125-7311
荒川上流河川事務所	川越市新宿町3-12	049-246-6371
埼玉県越谷県土整備事務所	越ヶ谷4-2-82	964-5221
熊谷地方気象台	熊谷市桜町1-6-10	048-521-0058
その他施設		
埼玉県越谷保健所	越谷市越ヶ谷4-2-26	964-1266
東京電力(株)埼玉カスタマーセンター	0120-995-442	
東京ガスお客様センター	0570-002211	
NTT東日本サービス運営部	0120-270-794	
NTT東日本(株) 埼玉支店 ※固定電話の故障時における連絡先	固定電話からは　113 携帯電話からは　0120-444-113	

問い合わせ先 ▶ **八潮市 環境経済部 交通防災課 防災係**
八潮市中央一丁目2番地1
TEL 048-996-2111 内線(305)　E-mail kotsubosai@city.yashio.lg.jp
ホームページ http://www.city.yashio.lg.jp/

荒川水系芝川・新芝川浸水想定区域図（八潮市）

避難場所一覧

番号	避難場所	所在地	電話番号
(1)	八條小学校	鶴ヶ曽根1	996-8400
(2)	潮止小学校	南川崎823	996-9955
(3)	八幡小学校	中央4-21-16	996-4042
(4)	大曽根小学校	圷490	996-6372
(5)	松之木小学校	緑町3-9-1	996-1377
(6)	中川小学校	大瀬1516	996-1375
(7)	八條北小学校	八條4150	931-3261
(8)	大瀬小学校	大瀬530	995-9321
(9)	大原小学校	八潮7-42-1	997-1028
(10)	柳之宮小学校	柳之宮140	995-6091
(11)	八潮中学校	中央1-1-2	996-4219
(12)	大原中学校	八潮5-9-1	996-1378
(13)	八條中学校	八條555	996-2121
(14)	八幡中学校	緑町4-19-1	997-1027
(15)	潮止中学校	古新田530	996-7325
(16)	八潮高校	鶴ヶ曽根650	996-1130
(17)	八潮南高校	南川崎519-4	995-5700
(18)	コミュニティセンター	八條665	936-0507
(19)	文化スポーツセンター	八潮3-31	996-5126
(20)	勤労青少年ホーム	南川崎523	996-0123
(21)	八幡公民館	中央3-32-11	995-6216
(22)	老人福祉センター寿楽荘	木曽根322	995-2847
(23)	資料館	南後谷763-50	997-6666
(24)	やしお生涯学習館	鶴ヶ曽根420-2	994-1000
(25)	八條公民館	八條2753-46	994-3200

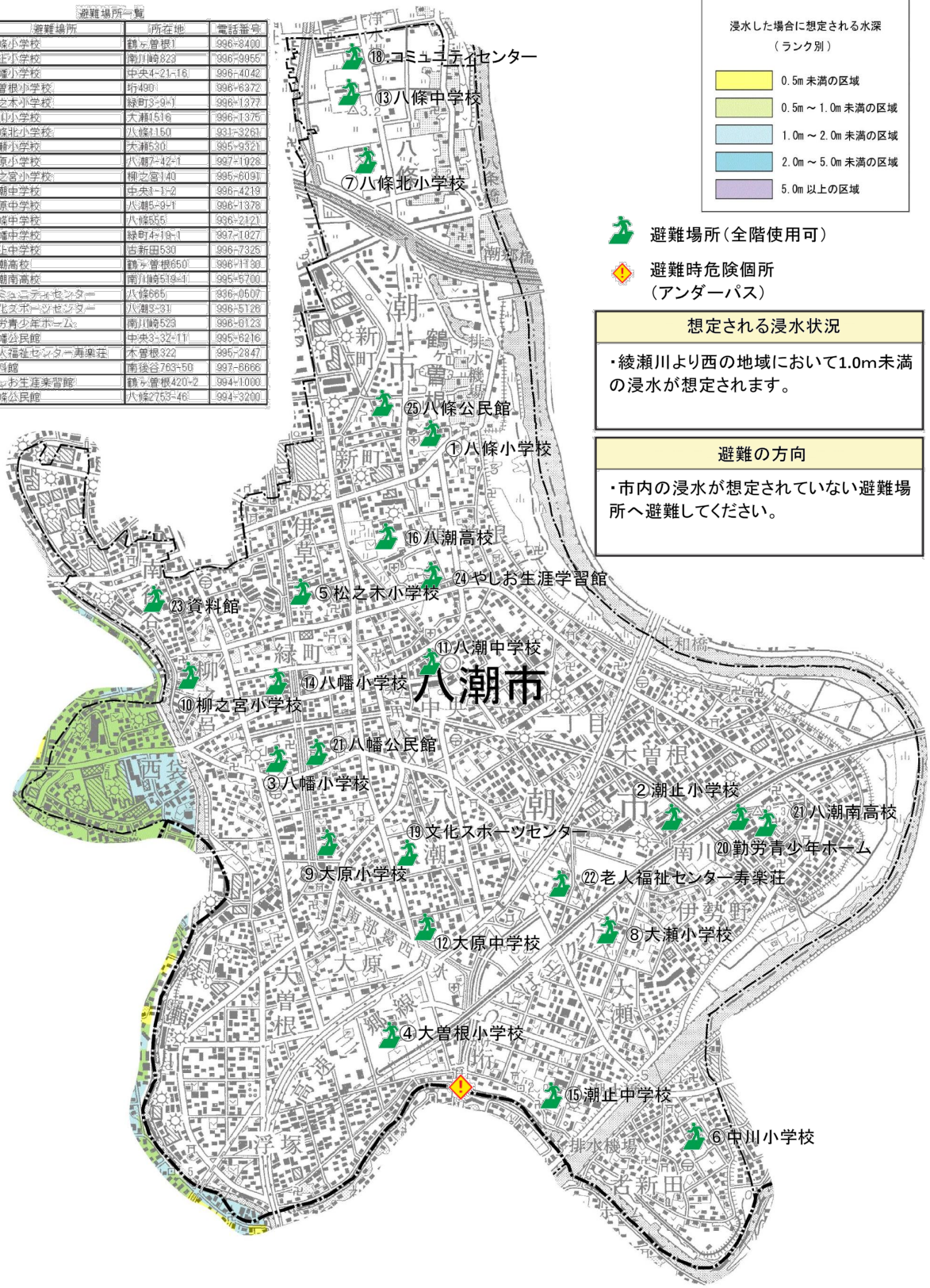

想定される浸水状況
・綾瀬川より西の地域において1.0m未満の浸水が想定されます。

避難の方向
・市内の浸水が想定されていない避難場所へ避難してください。

資料2.24 浸水想定区域内の特に防災上の配慮を要する者が利用する施設

（水防法第15条第１項第３号関係）

凡例：◎／通常通り利用可能　　○／２階以上が利用可能　　－／使用不可能

【保育園（公立）】

施設名	住所	利根川	江戸川	中川・綾瀬川・新方川	荒川	芝川・新芝川	元荒川・大落古利根川
八条保育園	八條1567	○	◎	◎	◎	◎	◎
伊草保育園	伊草372	－	◎	◎	◎	◎	◎
南川崎保育所	南川崎207-1	○	○	◎	○	◎	◎
古新田保育園	古新田10	－	○	－	－	◎	－
駅前保育所	大瀬795-1	－	－	◎	－	◎	◎
大曽根保育園	大曽根1518	－	－	◎	－	◎	◎
中馬場保育園	中央3-29-17	－	◎	◎	◎	◎	◎
中央保育園	八潮8-1-5	○	○	○	○	◎	○

【保育園（私立）】

施設名	住所	利根川	江戸川	中川・綾瀬川・新方川	荒川	芝川・新芝川	元荒川・大落古利根川
やしお花桃保育園	二丁目1067-1	－	－	◎	－	◎	◎
八潮かえで保育園	大瀬581-1	○	○	◎	○	◎	◎
けやきの森保育園	垰161-1	○	○	◎	○	◎	◎
八潮ひまわり保育園	中央1-15-5	◎	◎	◎	◎	◎	◎

【幼稚園】

施設名	住所	利根川	江戸川	中川・綾瀬川・新方川	荒川	芝川・新芝川	元荒川・大落古利根川
みひかり幼稚園	八條1760	○	○	○	○	◎	○
八潮ちくみ幼稚園	鶴ヶ曽根124	○	○	○	○	◎	○
潮止幼稚園	木曽根1063	－	○	◎	○	◎	◎
小倉あさひ幼稚園	大曽根536	－	－	◎	－	◎	◎
八潮幼稚園	西袋1218-2	－	－	◎	－	◎	◎
青和幼稚園	八潮4-4-3	－	◎	◎	◎	◎	◎

【障害福祉サービス事業者】

施設名	住所	利根川	江戸川	中川・綾瀬川・新方川	荒川	芝川・新芝川	元荒川・大落古利根川
やまびこ	鶴ヶ曽根403-1	－	◎	◎	◎	◎	◎
身体障害者福祉センターやすらぎ	鶴ヶ曽根414-1	－	◎	◎	◎	◎	◎
八潮市生活支援センターあけぼの	鶴ヶ曽根1130	○	◎	◎	◎	◎	◎
虹の家	鶴ヶ曽根1686-2	－	◎	◎	◎	◎	◎
わかくさ	南川崎826-3	○	○	◎	○	◎	◎
工房森のこかげ	緑町2-13-13	－	◎	◎	◎	◎	◎
mirai	緑町2-17-4 東武マンション1F南	－	◎	◎	◎	◎	◎

【高齢者福祉事業者】

施設名	住所	利根川	江戸川	中川・綾瀬川・新方川	荒川	芝川・新芝川	元荒川・大落古利根川
デイサービスぽっかぽか	八條50	○	◎	◎	○	◎	◎
グループホームぽっかぽか	八條50	○	◎	◎	○	◎	◎
シルバータウンやしお	八條90-1	○	○	○	○	◎	○
デイサービスセンター やしお寿苑	八條294-4	－	－	○	○	◎	○
総合福祉ツクイ八潮	八條1567 八潮団地22-101	－	◎	◎	◎	◎	◎
ヴィレクール	八條2627	－	－	－	◎	◎	－
あずみ苑八潮	八條3636-1	○	○	○	◎	◎	○
特別養護老人ホーム 杜の家やしお	鶴ヶ曽根567-1	○	◎	◎	◎	◎	◎
ケアセンター八潮	鶴ヶ曽根1184-4	○	◎	◎	◎	◎	◎
茶話本舗デイサービス センター八潮草加	伊草87-8	◎	◎	◎	◎	◎	◎
ふるさとホーム八潮	南川崎132-2	○	○	◎	◎	◎	◎
高齢者福祉施設やしお苑	南川崎210-1	○	○	◎	○	◎	◎
(医)福寿会 埼玉回生病院	大原455	○	○	◎	○	◎	◎
愛の家グループホーム八潮	大曽根1273-1	○	○	◎	○	◎	◎
八潮ケアセンターそよかぜ	中央3-1-2	○	◎	◎	◎	◎	◎
デイサービスセンター 癒し処はるかぜ	中央3-10-13	○	◎	◎	◎	◎	◎
民家型デイサービスほおずき	緑町1-5-2	○	◎	◎	◎	◎	◎
グループホーム八潮	緑町1-23-8	○	◎	◎	◎	◎	◎

【医療機関】

施設名	住所	利根川	江戸川	中川・綾瀬川・新方川	荒川	芝川・新芝川	元荒川・大落古利根川
中央総合病院	緑町1-41-3	○	◎	◎	◎	◎	◎
広瀬病院	八條2840-1	○	○	○	◎	◎	○
(医)福寿会 埼玉回生病院	大原455	○	○	◎	○	◎	◎
南後谷診療所	南後谷751	○	○	◎	○	◎	◎
八潮病院	鶴ヶ曽根1089	○	◎	◎	◎	◎	◎